Stratégie d’expansion internationale

Pays à fort potentiel pour l’export de volaille

COMEX La Poule qui chante

Anthony Rake
Data Analyst
17/10/2025

Préparation des données

1) Sources mobilisées :

- FAO (production, import/export de poulet)
- Banque mondiale (PIB, croissance, stabilité politique, urbanisation, climat des affaires)
- CEPII (distance géographique)

2) Approche PESTEL :

- Sélection de 9 variables couvrant les dimensions Politique, Économique, Socioculturelle, Commerciale et Environnementale.

Axe PESTEL	Variable sélectionnée
Économique	PIB par habitant, croissance du PIB, import/export de poulet, production de poulet
Politique	Indice de stabilité politique
Commercial	Indice Doing Business
Environnemental	Distance avec la France
Socioculturel	Part de la population urbaine

Constitution du jeu de données

1) Nettoyage et harmonisation :

- Normalisation des clés primaires (Country Code)
- Sélection de l'année 2018 comme référence commune (meilleure couverture hors période Covid)
- Renommage des colonnes pour faciliter les jointures

2) Fusion des datasets :

- Jointure progressive autour de la population
- Création d'un fichier unique avec 10 variables quantitatives + 1 identifiant pays

3) Couverture obtenue :

- Pays inclus : 119
- Population mondiale couverte : > 90%
- Taux de complétude par variable : 100%

Démarche d'analyse

1) Standardisation des variables

- Mettre toutes les données (PIB, croissance, stabilité, etc.) sur une même échelle pour les comparer sans biais.

2) Analyse en Composantes Principales (ACP)

- Réduire la complexité des données et identifier les grands axes explicatifs :
  Axe 1 : dimension économique | Axe 2 : dimension institutionnelle / accessibilité

3) Clustering hiérarchique (CAH)

- Regrouper les pays selon leurs profils similaires (méthode de Ward) et repérer les grands types de marchés.

4) Clustering K-means

- Valider les regroupements précédents par une méthode complémentaire (partition en 3 groupes homogènes).

5) Croisement des deux approches et hiérarchisation finale

- Retenir uniquement les pays cohérents dans les deux classifications : **47 pays à fort potentiel.**

Analyses par Composantes Principales (ACP)

Combien de composantes principales et que représentent-elles ?

2 composantes retenues

L'analyse de **l'éboulis** montre que les deux premières composantes expliquent une part importante de **l'information initiale (environ 65 %).**

PC1 : dimensions économiques

Les variables économiques (PIB, export, production, import) sont fortement corrélées entre elles et définissent **l'axe 1, représentant la dimension économique.**

PC2 : dimensions institutionnelles

Les indicateurs institutionnels (stabilité politique, doing business, urbanisation) s'alignent sur **l'axe 2, traduisant la dimension d'accessibilité et de gouvernance.**

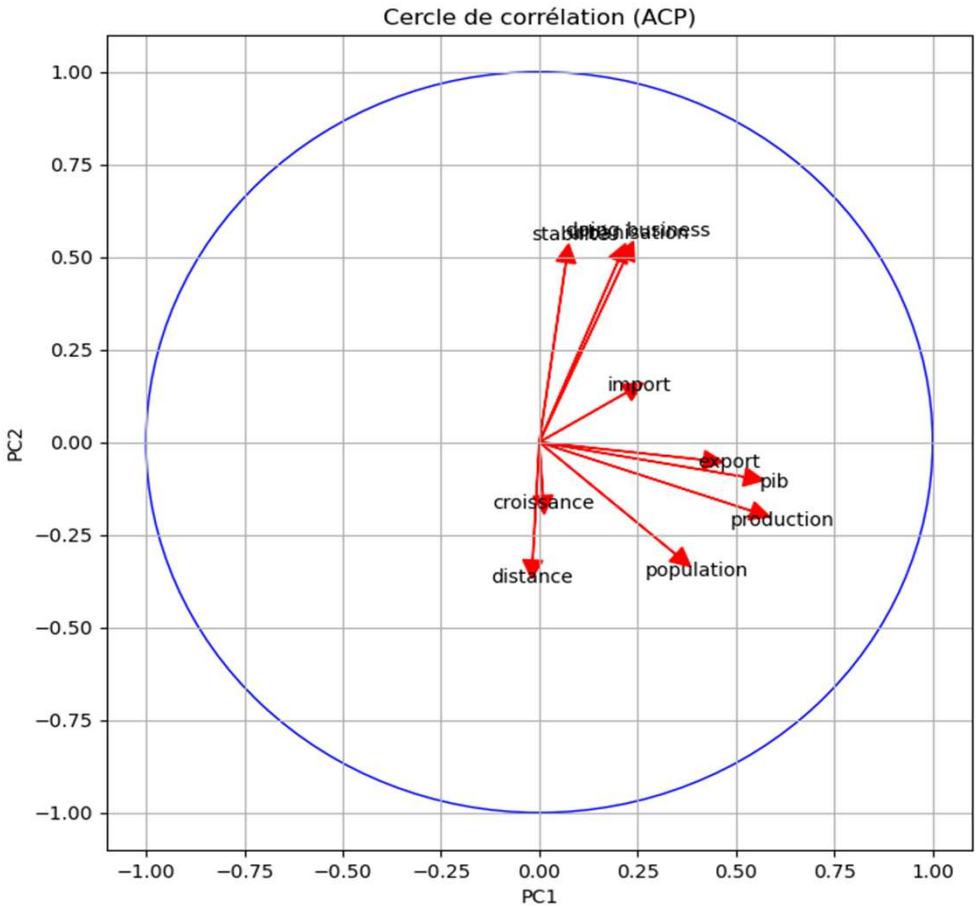

Projection des pays (plan factoriel)

Situer les pays selon leurs profils économiques et institutionnels

Les pays à forte dimension économique (PIB, production, export) se situent à droite du graphique — États-Unis, Chine, Brésil.

Les pays stables et urbanisés apparaissent en haut, traduisant une meilleure accessibilité institutionnelle.

Cette projection offre une vision d'ensemble claire des profils pays, avant la phase de regroupement par similarité.

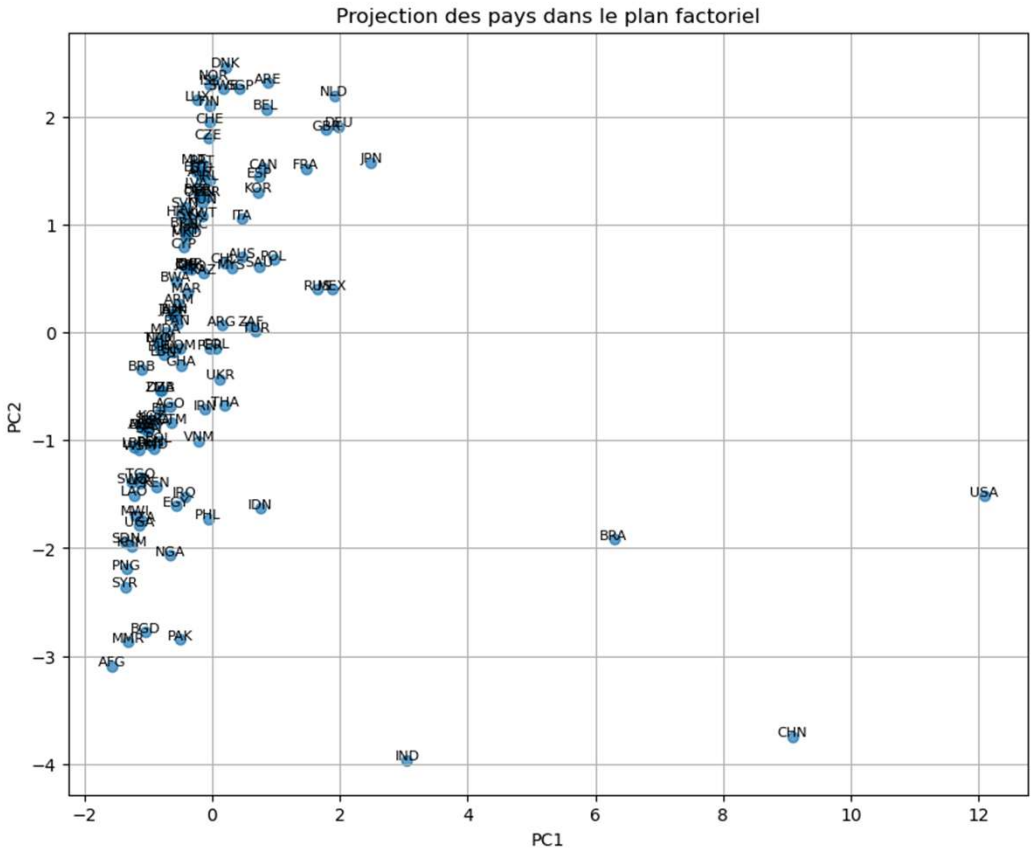

Clustering hiérarchique (CAH)

Regroupement des pays aux profils proches

Quatre groupes distincts apparaissent, reflétant des niveaux différents de développement et d'accessibilité.

L'un des groupes se distingue par **des marchés matures, stables et proches de la France**, premiers candidats à l'export.

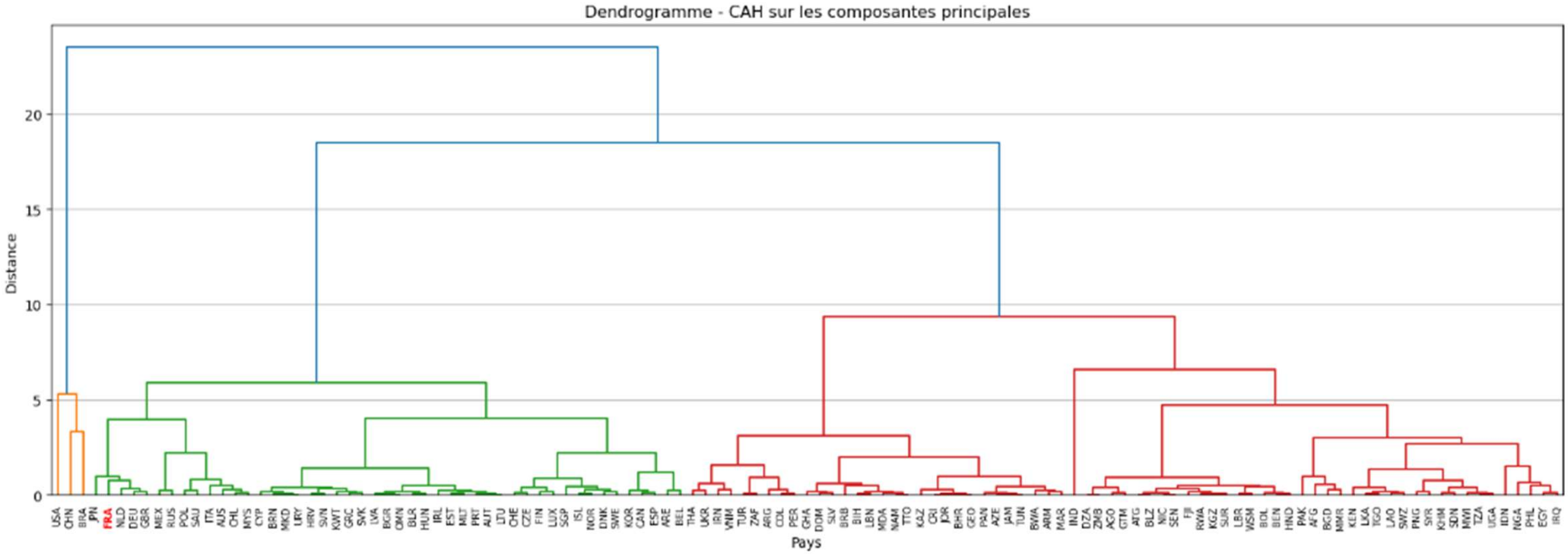

Projection des clusters CAH

Visualisation des clusters et des pays qui les composent

Un groupe de **grandes puissances** (États-Unis, Chine, Inde, Brésil) se distingue nettement par leur poids économique.

Les **pays développés stables** (cluster 2) combinent croissance, stabilité et accessibilité, en faisant la base de la **shortlist potentielle**.

Les autres groupes rassemblent des marchés en développement ou plus éloignés, présentant un potentiel moindre à court terme.

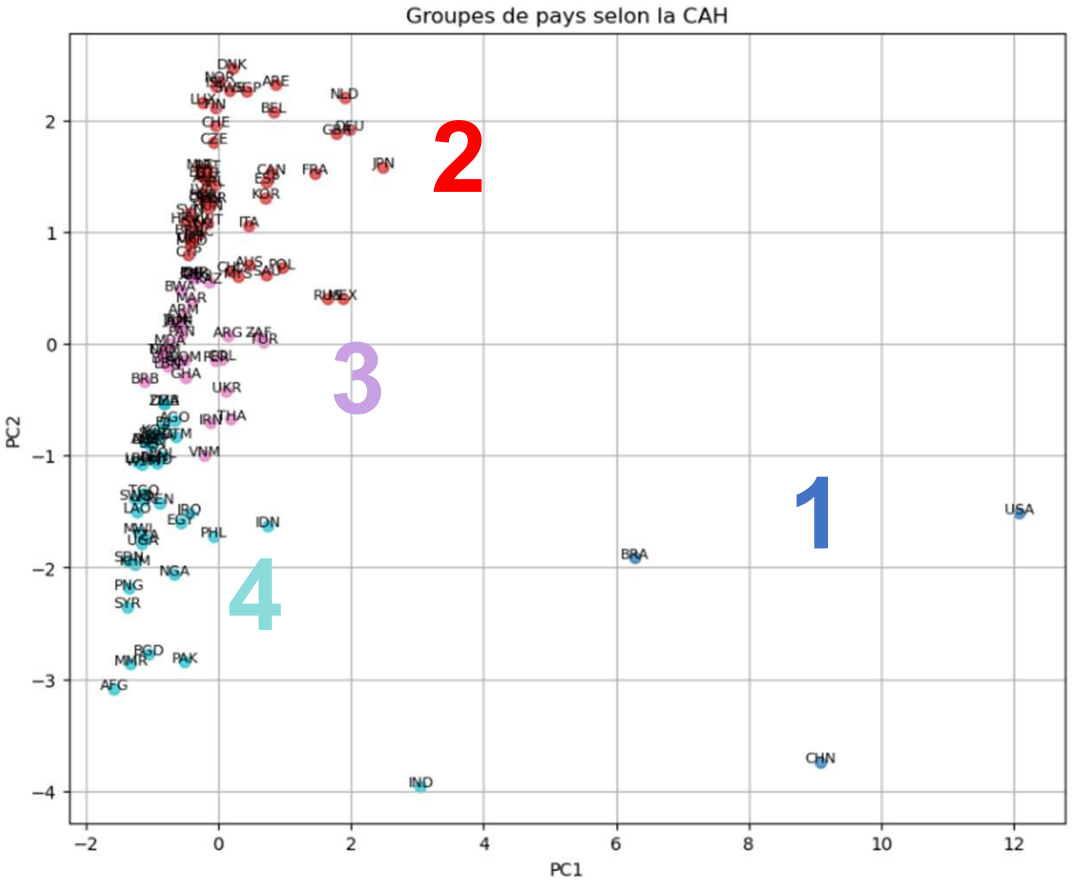

Clustering K-means

Regroupement des pays en ensembles homogènes

La méthode du coude montre une amélioration marquée jusqu'à k = 3.
Le choix de 3 clusters permet une segmentation pertinente sans complexifier inutilement le modèle.

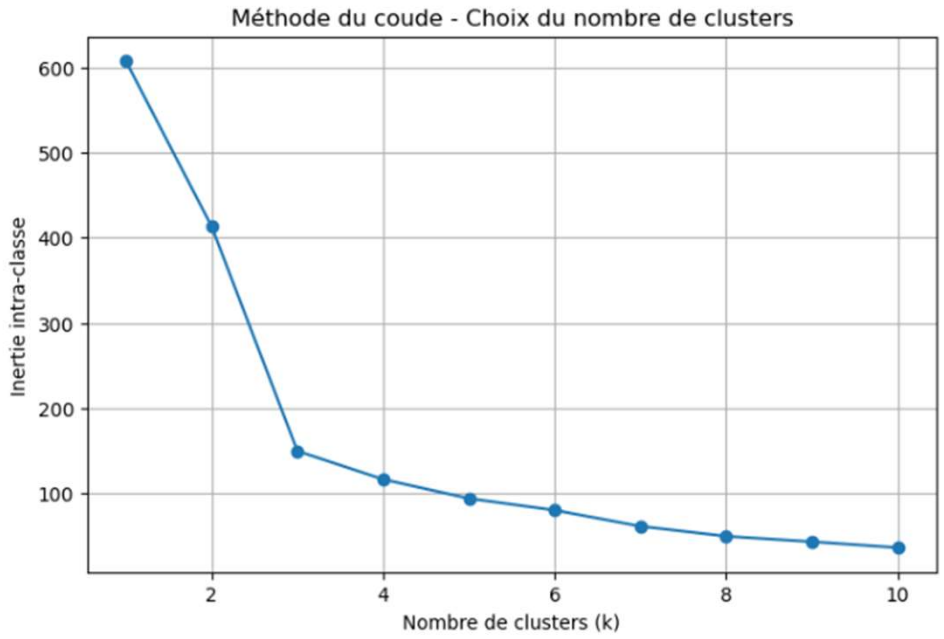

Le choix de 3 clusters permet de distinguer :
Cluster rouge : caractéristiques équilibrées
Cluster bleu : spécificités marquées
Cluster jaune : caractéristiques extrêmes

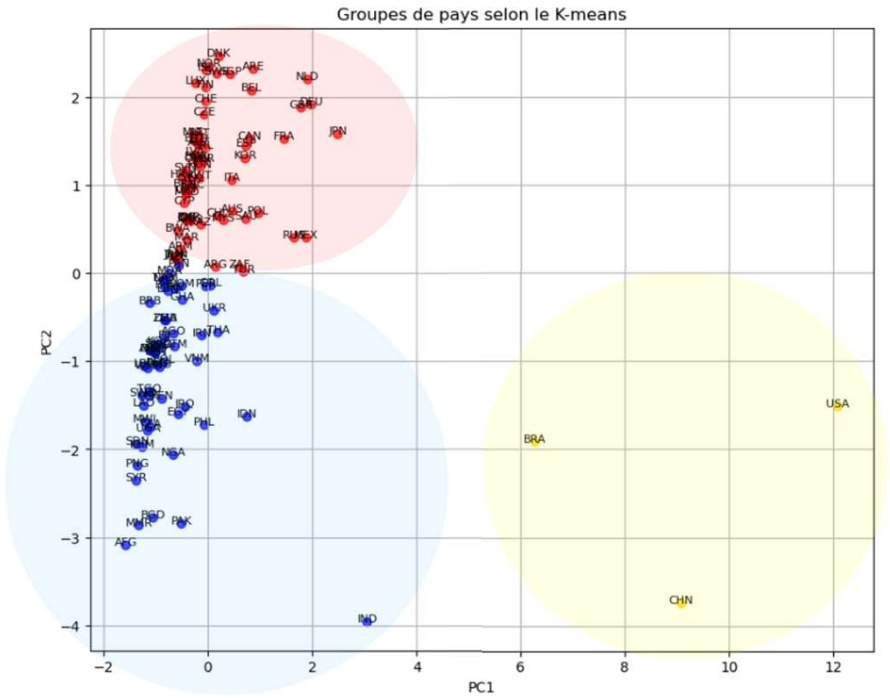

Analyse des clusters

4 clusters issus de la CAH

Cluster 1 – Grands marchés développés et éloignés

Population très importante, économies puissantes, niveaux élevés d'exportations, de production et d'importations, marchés ouverts, urbanisation avancée, éloignement géographique marqué.

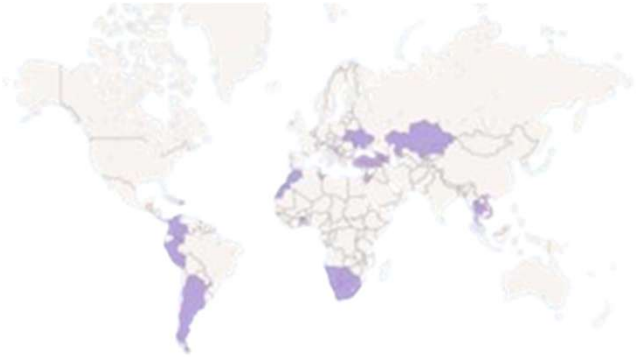

Cluster 3 – Marchés éloignés et instables

Population intermédiaire, économies en développement, échanges commerciaux limités, urbanisation moyenne, instabilité politique marquée, éloignement géographique significatif.

Cluster 4 – Petits marchés en difficulté et éloignés

Hormis l'Inde, population limitée, économies fragiles, échanges commerciaux faibles, production réduite, urbanisation peu développée, environnement des affaires peu favorable, instabilité marquée, éloignement géographique important.

Analyse des clusters

4 clusters issus de la CAH

Cluster 2 – Marchés proches et stables (47 pays)

- Population moyenne
- PIB intermédiaire
- Croissance bonne (~2.9 %)
- Production moyenne
- Export/import moyens
- Stabilité forte (0.64)
- Urbanisation et Doing Business élevés (~78)
- Distance major. faible (~3600 km)

Il s'agit de marchés **accessibles, stables et en développement.**

Avantage : proximité géographique, environnement favorable aux affaires, stabilité.

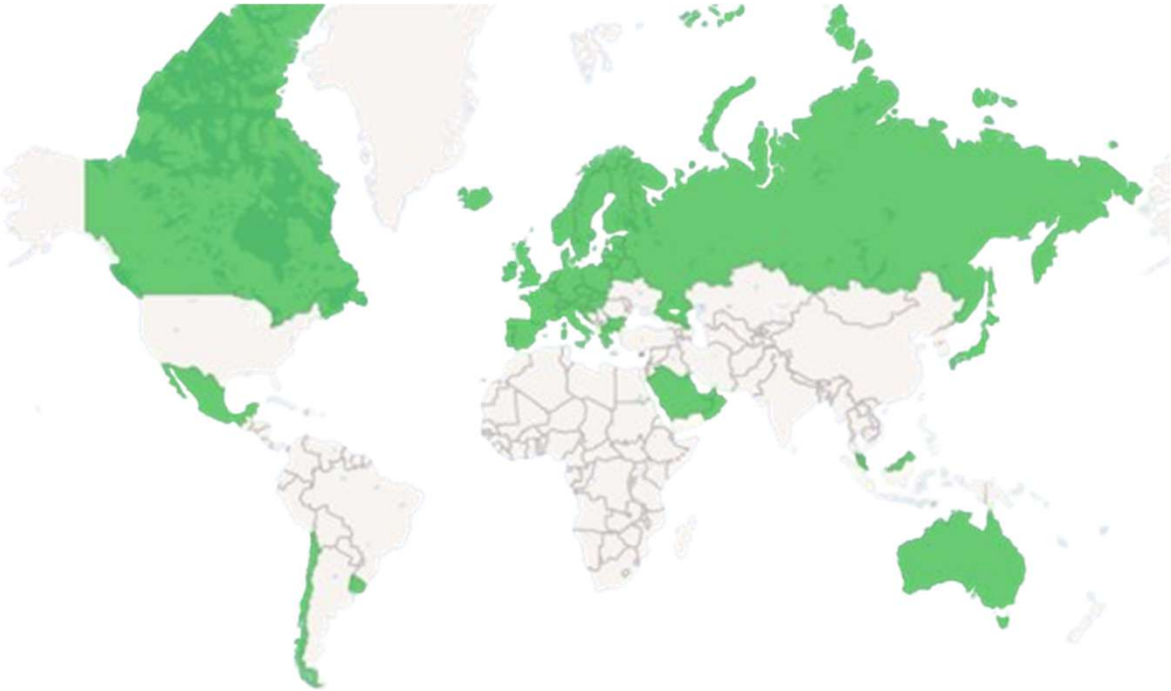

Les pays membres de l'Union européenne incluent l'Autriche, la Belgique, la Bulgarie, Chypre, la Tchéquie, l'Allemagne, le Danemark, l'Espagne, l'Estonie, la Finlande, la France, la Grèce, la Croatie, la Hongrie, l'Irlande, l'Italie, la Lituanie, le Luxembourg, la Lettonie, Malte, les Pays-Bas, la Pologne, le Portugal, la Slovaquie, la Slovénie et la Suède.
Les pays hors Union européenne comprennent les Émirats arabes unis, l'Australie, le Bélarus, le Brunei, le Canada, la Suisse, le Chili, le Royaume-Uni, l'Islande, le Japon, la Corée du Sud, le Koweït, le Mexique, la Macédoine du Nord, la Malaisie, la Norvège, Oman, la Russie, l'Arabie saoudite, Singapour et l'Uruguay.

Analyse des clusters

3 clusters issus du K-means

Cluster 0 – Marchés intermédiaires éloignés et moyennement développés

Population importante, niveau de développement intermédiaire, échanges commerciaux limités, production modérée, urbanisation faible, environnement des affaires acceptable mais pas optimale, instabilité politique notable, éloignement géographique marqué.

Cluster 2 – Grands marchés développés et éloignés

Population très importante, économies puissantes, échanges commerciaux et production à très haut niveau, urbanisation avancée, environnement des affaires favorable, stabilité modérée, éloignement géographique marqué.

Analyse des clusters

3 clusters issus du K-means

Cluster 1 – Marchés émergents proches et stables (61 pays)

- Population intermédiaire
- Niveau de développement bon
  Echanges commerciaux bons
  Production bonne
- Urbanisation avancée,
  Environnement des affaires favorable,
- Bonne stabilité politique,
- Proximité géographique

Avantage : proximité géographique, stabilité politique, environnement favorable aux affaires.

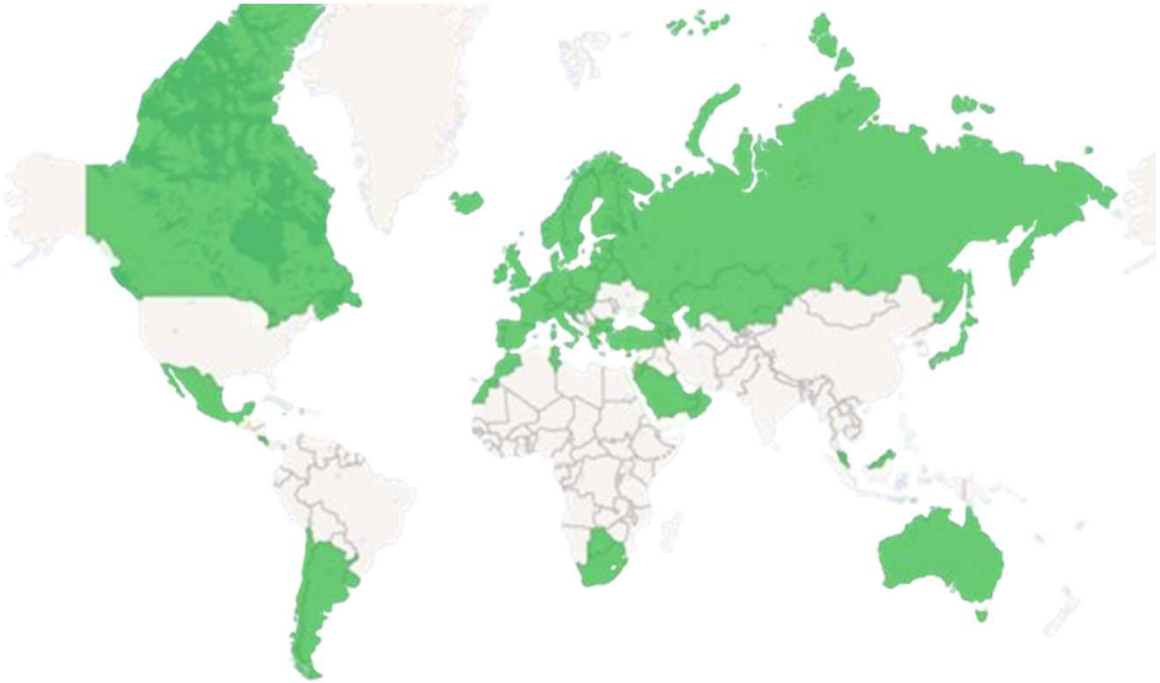

Les pays membres de l'Union européenne présents dans ce cluster incluent l'Autriche, la Belgique, la Bulgarie, la Croatie, Chypre, la Tchéquie, le Danemark, l'Estonie, la Finlande, la France, l'Allemagne, la Grèce, la Hongrie, l'Irlande, l'Italie, la Lettonie, la Lituanie, le Luxembourg, Malte, les Pays-Bas, la Pologne, le Portugal, la Slovaquie, la Slovénie, l'Espagne et la Suède.
Les pays hors Union européenne regroupent les Émirats arabes unis, l'Argentine, l'Arménie, l'Australie, l'Azerbaïdjan, Bahreïn, le Bélarus, le Brunei, le Botswana, le Canada, la Suisse, le Chili, le Costa Rica, la Géorgie, l'Islande, la Jamaïque, la Jordanie, le Japon, le Kazakhstan, la Corée du Sud, le Koweït, la Malaisie, le Mexique, le Maroc, la Macédoine du Nord, la Norvège, Oman, la Russie, l'Arabie saoudite, Singapour, la Tunisie, la Turquie, l'Uruguay et l'Afrique du Sud.

Recommandation

47 pays retenus : stabilité, performance économique, environnement favorable

1/ Point de départ : les pays membres de l'Union européenne – proches, stables et bien intégrés (26 pays)
Austria, Belgium, Bulgaria, Croatia, Cyprus, Czechia, Denmark, Estonia, Finland, Germany, Greece, Hungary, Ireland, Italy, Latvia, Lithuania, Luxembourg, Malta, Netherlands, Poland, Portugal, Slovak Republic, Slovenia, Spain, Sweden

2/ Pays hors UE mais stables, à haut revenu et historiquement liés à l'Europe (9 pays)
United Kingdom, Norway, Switzerland, Iceland, Canada, Australia, Japan, Korea, Rep., Singapore
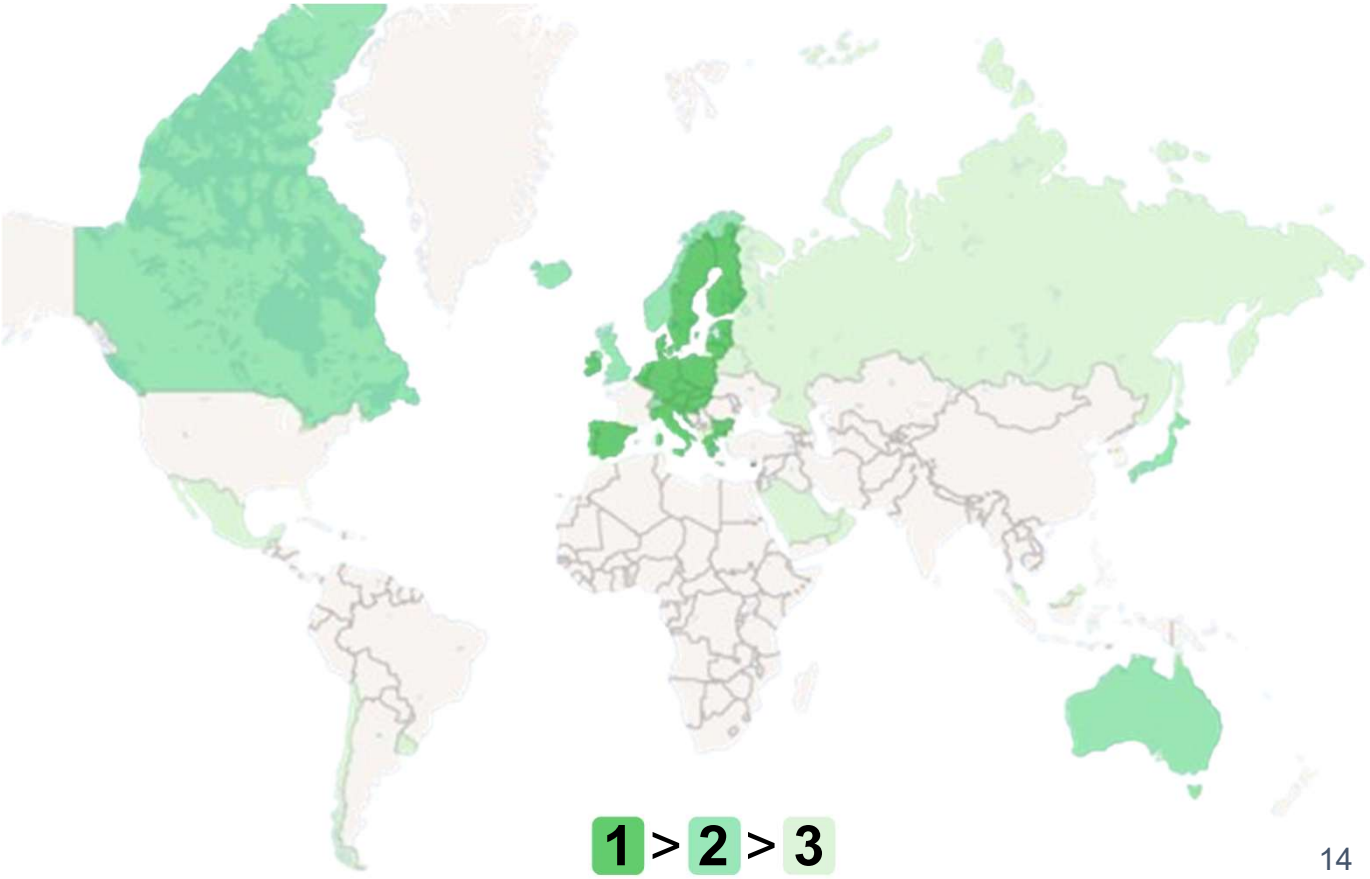
3/ Pays performants mais plus éloignés géographiquement ou institutionnellement (12)
Belarus, Brunei Darussalam, Chile, Kuwait, Malaysia, Mexico, North Macedonia, Oman, Russian Federation, Saudi Arabia, United Arab Emirates, Uruguay